펫 버디 앱 기획안

Follow the latest trends

With our pet walking app

Jeong yu jin 98@buddy.com Submit

9:41 AM
100%
pet
시작하기

INDEX

1. 기획
2. 설계
3. 분석
4. 마무리

기획 배경

반려동물을 위해 세심하고 체계적인 라이프 스타일을 제공하고자 하는반려인 증가
→기존에 제공되고 있는 정보보다 더 세심하고 체계적인, 반려동물 맞춤 서비스를 찾는 사용자 증가

코로나 19 바이러스 이후, 개인/소규모 생활이 자리를 잡게 되면서 사회와의 단절로 인한 외로움, 고립감 급증
→반려가구 수의 지속적인 증가

PET
반려동물
+
FAMily
가족
펫팸족 Pet + Family
펫미족 Pet = Me

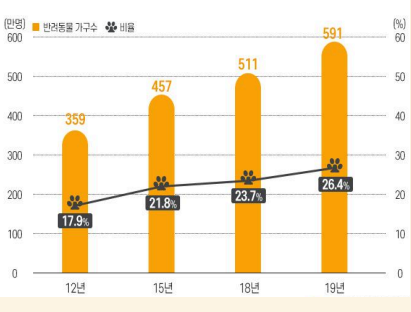

단순 위치 기반 앱이 아닌
사용자의 반려동물 특성과 실제 이용 데이터를 결합한
맞춤형 산책 의사결정 플랫폼을 기획하고자 합니다.

앱 이름 : 펫 버디 (PET BUDDY)

앱 로고 의미

버디는 친근한 관계를 뜻하는 단어로
나와 반려동물의 관계가 단짝친구라는 것을 의미함.



반려인과 반려동물의 악수는 서로에 대한 사랑과 신뢰를 보여줌.

페르소나

니즈	핵심 기능	문제점
• 반려견 맞춤 운동 관리 • 정확한 데이터 기반 건강 체크 • 효율적인 기록 관리	• 반려동물 맞춤 산책로 추천 (크기/건강 상태 기반) • 산책 자동 기록 + 운동량 분석 리포트 • 목표 설정 기반 루틴 관리 기능	• 적합한 산책 강도와 코스를 판단하기 어려움 • 안전한 산책 환경에 대한 정보 부족

니즈	핵심 기능	문제점
• 반려인 간 소통 • 산책 메이트 연결 • 콘텐츠 공유	• 지역 기반 산책 메이트 매칭 기능 • 커뮤니티 피드 (사진/후기 공유) • 산책 모임 생성 및 참여 기능	• 함께 산책할 수 있는 메이트를 찾기 어려움

니즈	핵심 기능	문제점
• 쉬운 산책로 탐색 • 안전 정보 제공 • 대형견 맞춤 코스	• 위치 기반 간편 산책로 추천 (원클릭 탐색) • 안전 정보 표시 (혼잡도, 위험 요소 등) • 반려견 크기 기반 필터 기능	• 대형견에게 적합한 산책로 정보를 찾기 어려움

요구사항 및 서비스 도출

요구사항 분석

1. 사용자의 현재 위치를 기반으로 주변 산책로를 자동 탐색 및 추천해야 한다.
2. 반려동물의 크기, 나이에 따라 적합한 산책로를 필터링할 수 있어야 한다.
3. 각 산책로에 대해 아래 정보를 제공해야 한다.
- 거리 / 소요시간
- 난이도
- 경로시설정보
4. 산책로 내 위험 요소를 사전에 확인할 수 있어야 한다.
- 안전도
- 반려동물 제한 구역
5. 사용자의 산책 데이터가 기록 및 저장돼야 한다.
- 이동 거리 / 시간 / 칼로리 / 경로
6. 반려동물의 건강 데이터를 지속적으로 기록 및 관리할 수 있어야 한다.
- 체중 변화
- 운동량
7. 산책 활동에 따라 포인트 및 보상을 제공해야 한다.
- 목표 달성 보상
- 꾸준한 활동 보상
8. 사용자가 최소한의 조작으로 원하는 정보를 얻을 수 있어야 한다.
- 앱 실행 시 바로 추천 화면 제공
- 간단한 필터 구조
- 지도 기반 직관적 탐색

앱 서비스

1. 위치 기반 산책로 자동 추천
2. 반려동물 맞춤 필터링 기능
3. 산책로 상세 정보 제공
4. 안전 정보 및 위험 요소 표시
5. 산책 기록 저장 기능
6. 반려동물 건강 관리 기능
7. 리워드 및 동기부여 시스템
8. 빠르고 직관적인 UX/UI

핵심 및 선택 기능

- 핵심 기능
1. 위치 기반 산책로 추천
2. 반려동물 맞춤 필터
3. 안전/혼잡도 정보
4. 산책 기록 (기본)
- 선택 기능 (확장)
1. 커뮤니티
2. 모임/매칭
3. 리워드

불필요 기능

1. 복잡한 데이터 리포트
2. 과도한 필터 구조 (자동 매칭)
3. 기능 과잉 UI

스타일 가이드

폰트 사이즈

포인트 폰트 : Gamga flower

가나다라마바사
가나다라마바사
가나다라마바사

ABCDEFG
ABCDEFG
ABCDEFG

서브 폰트 : Alexandria

가나다라마바사 **가나다라마바사**
가나다라마바사 가나다라마바사 **가나다라마바사**
가나다라마바사

ABCDEFG **ABCDEFG**
ABCDEFG ABCDEFG **ABCDEFG**
ABCDEFG

폰트 컬러

#4CAF88
#69A99F
#FBAA99
#FFE17E
#757575

포인트 컬러

#4CAF88

메인 컬러

#FFFAE5

서브 컬러

#FFE3AA
#FCCE65
#F1DF85
#FBAA99

버튼 컬러

#D9D9D9
#D9D9D9
#69A99F
#FDEFD2
#D9D9D9
#FFFAE5
#FBAA99
#FFE3AA

무드보드

키워드 : 따뜻한, 친근한, 포근한, 자연적인, 밝은

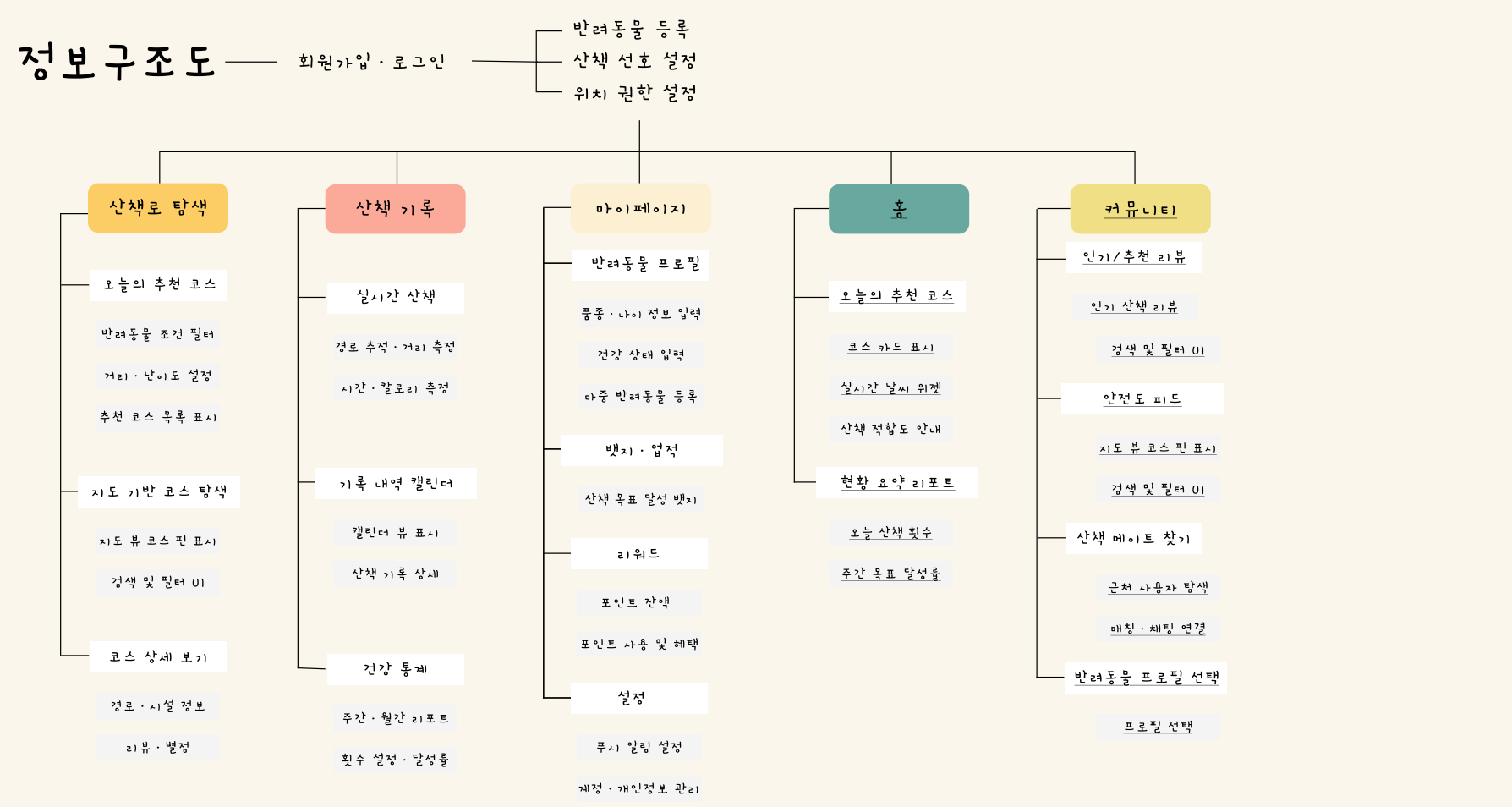

정보구조도

- 회원가입 · 로그인
  - 반려동물 등록
  - 산책 선호 설정
  - 위치 권한 설정
- 산책로 탐색
  - 오늘의 추천 코스
    - 반려동물 조건 필터
    - 거리 · 난이도 설정
    - 추천 코스 목록 표시
  - 지도 기반 코스 탐색
    - 지도 뷰 코스 핀 표시
    - 검색 및 필터 UI
  - 코스 상세 보기
    - 경로 · 시설 정보
    - 리뷰 · 별점
- 산책 기록
  - 실시간 산책
    - 경로 추적 · 거리 측정
    - 시간 · 칼로리 측정
  - 기록 내역 캘린더
    - 캘린더 뷰 표시
    - 산책 기록 상세
  - 건강 통계
    - 주간 · 월간 리포트
    - 횟수 설정 · 달성률
- 마이페이지
  - 반려동물 프로필
    - 품종 · 나이 정보 입력
    - 건강 상태 입력
    - 다중 반려동물 등록
  - 뱃지 · 업적
    - 산책 목표 달성 뱃지
  - 리워드
    - 포인트 잔액
    - 포인트 사용 및 혜택
  - 설정
    - 푸시 알림 설정
    - 계정 · 개인정보 관리
- 홈
  - 오늘의 추천 코스
    - 코스 카드 표시
    - 실시간 날씨 위젯
    - 산책 적합도 안내
  - 현황 요약 리포트
    - 오늘 산책 횟수
    - 주간 목표 달성률
- 커뮤니티
  - 인기/추천 리뷰
    - 인기 산책 리뷰
    - 검색 및 필터 UI
  - 안전도 피드
    - 지도 뷰 코스 핀 표시
    - 검색 및 필터 UI
  - 산책 메이트 찾기
    - 근처 사용자 탐색
    - 매칭 · 채팅 연결
  - 반려동물 프로필 선택
    - 프로필 선택

워크 플로우

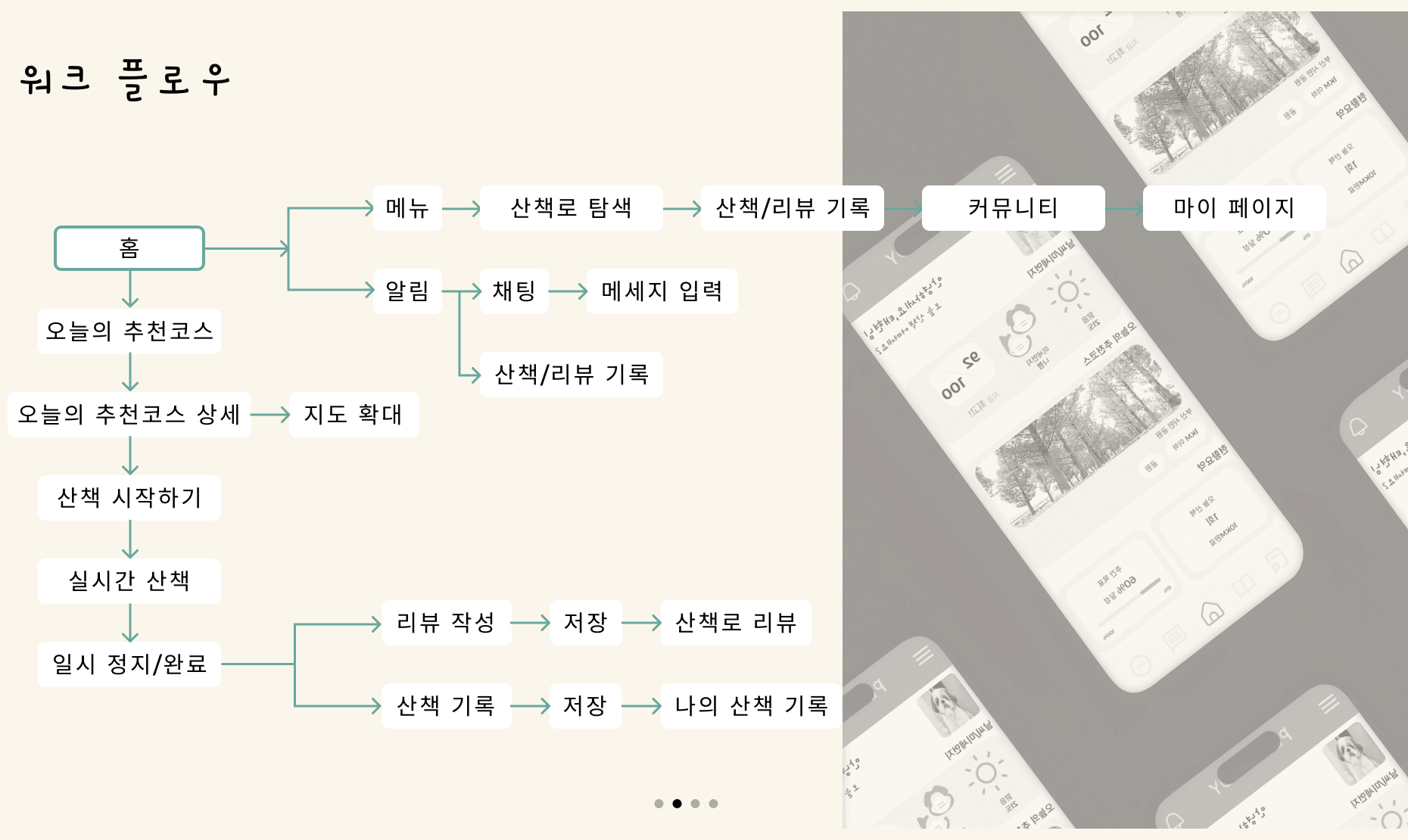

홈 → 메뉴 → 산책로 탐색 → 산책/리뷰 기록 → 커뮤니티 → 마이 페이지

홈 → 알림 → 채팅 → 메세지 입력

채팅 → 산책/리뷰 기록

홈 → 오늘의 추천코스 → 오늘의 추천코스 상세 → 지도 확대

오늘의 추천코스 상세 → 산책 시작하기 → 실시간 산책 → 일시 정지/완료

일시 정지/완료 → 리뷰 작성 → 저장 → 산책로 리뷰

일시 정지/완료 → 산책 기록 → 저장 → 나의 산책 기록

아이디어 스케치

와이어프레임

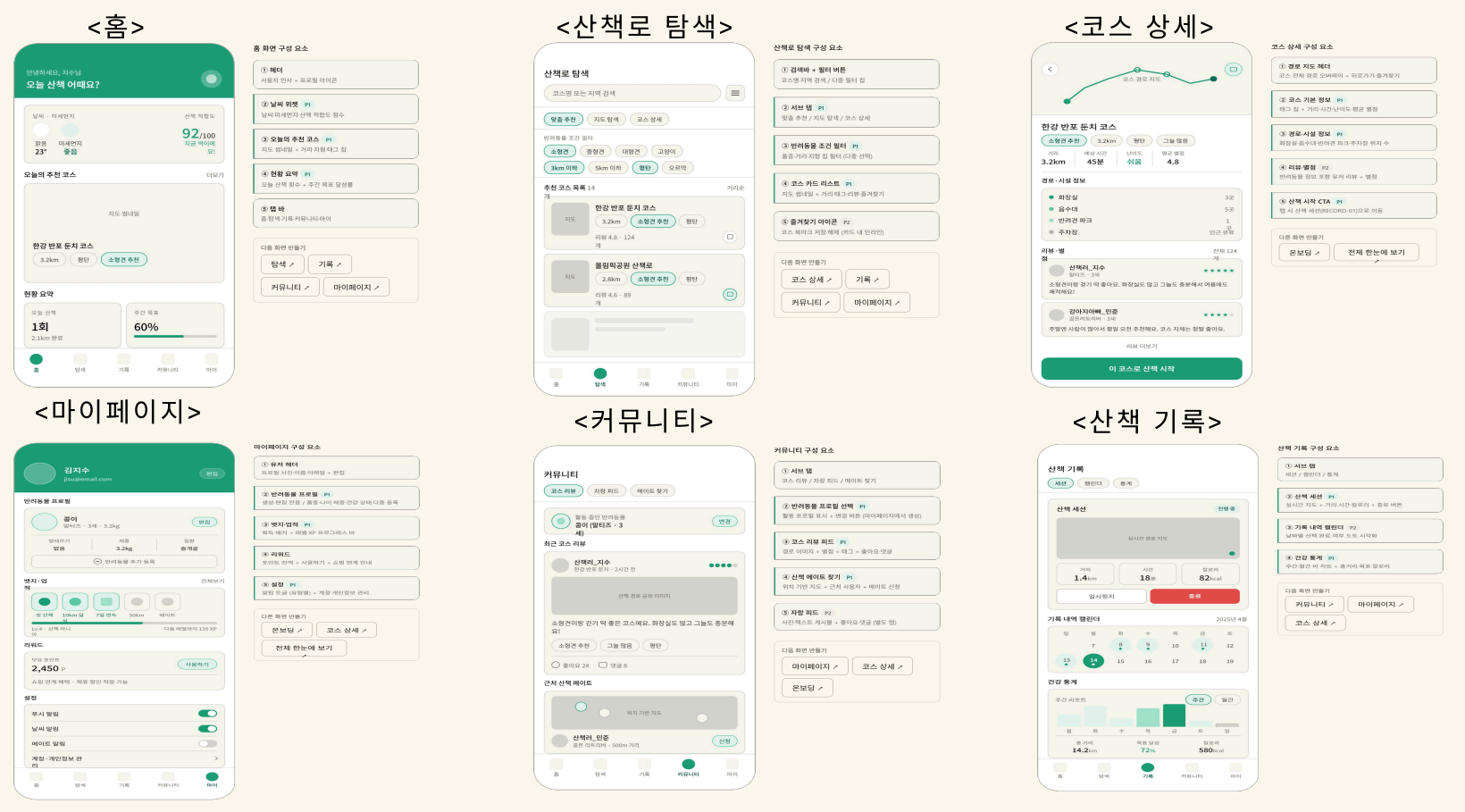
<홈>
<산책로 탐색>
<코스 상세>
<마이페이지>
<커뮤니티>
<산책 기록>

UI 디자인 시안

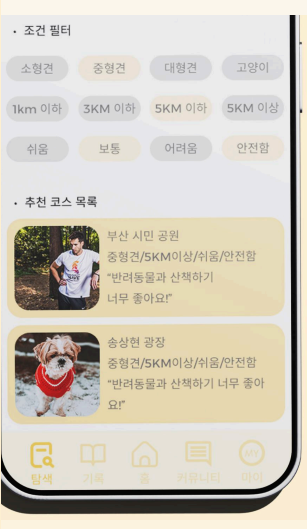
조건 필터
소형견
중형견
대형견
고양이
1km 이하
3KM 이하
5KM 이하
5KM 이상
쉬움
보통
어려움
안전함
추천 코스 목록

부산 시민 공원
중형견/5KM이상/쉬움/안전함
"반려동물과 산책하기 너무 좋아요!"

송상현 광장
중형견/5KM이상/쉬움/안전함
"반려동물과 산책하기 너무 좋아요!"

디자인 컨셉
따뜻하고 편안한 감성 + 직관적 UI + 앱 접근성

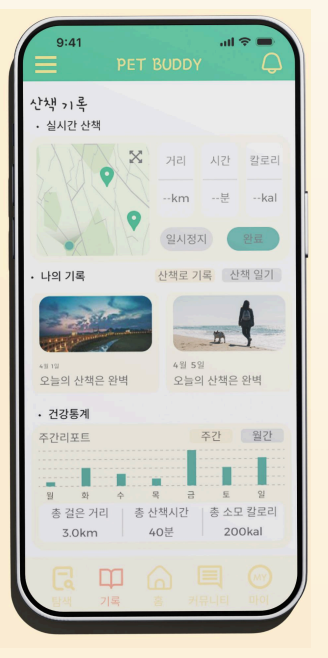
9:41
PET BUDDY
산책 기록
실시간 산책
거리
시간
칼로리
--km
--분
--kal
일시정지
완료
나의 기록
산책로 기록
산책 일기
4월 1일
4월 5일
건강통계
주간리포트
주간
월간
월
화
수
목
금
토
일
총 걸은 거리
총 산책시간
총 소모 칼로리
3.0km
40분
200kal

오늘의 산책은 완벽

UI 구성
상단 : 메뉴와 알림
중단 : 앱 서비스 버튼
하단 : 메뉴 선택

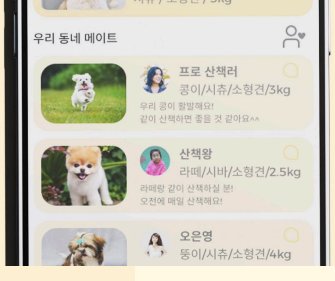
9:41
PET BUDDY
커뮤니티
인기/추천 리뷰
안전도 피드
메이트 찾기
: 정유진
: 쿠키
우리 동네 메이트

시츄 / 소형견 / 3kg

프로 산책러
콩이/시츄/소형견/3kg
우리 콩이 활발해요!
같이 산책하면 좋을 것 같아요^^

산책왕
라떼/시바/소형견/2.5kg
라떼랑 같이 산책하실 분!
오전에 매일 산책해요!

오은영
뚱이/시츄/소형견/4kg

디자인 특징
전 연령층을 위한 직관적 UI + 사용자 앱 접근성

① START

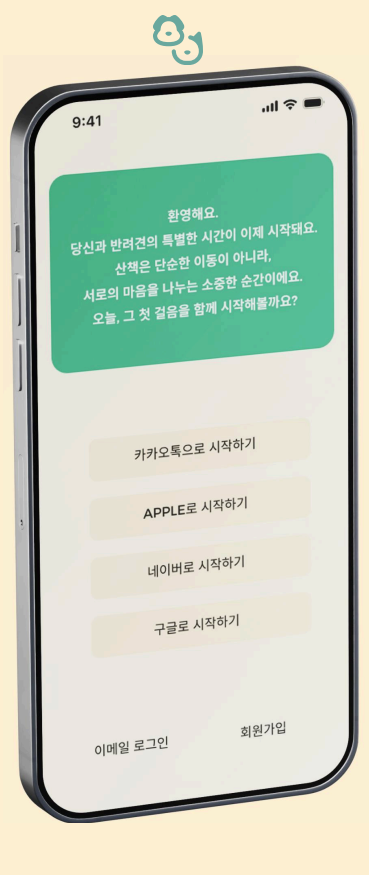
9:41
카카오톡으로 시작하기
APPLE로 시작하기
네이버로 시작하기
구글로 시작하기
이메일 로그인
회원가입

환영해요.
당신과 반려견의 특별한 시간이 이제 시작돼요.
산책은 단순한 이동이 아니라,
서로의 마음을 나누는 소중한 순간이에요.
오늘, 그 첫 걸음을 함께 시작해볼까요?

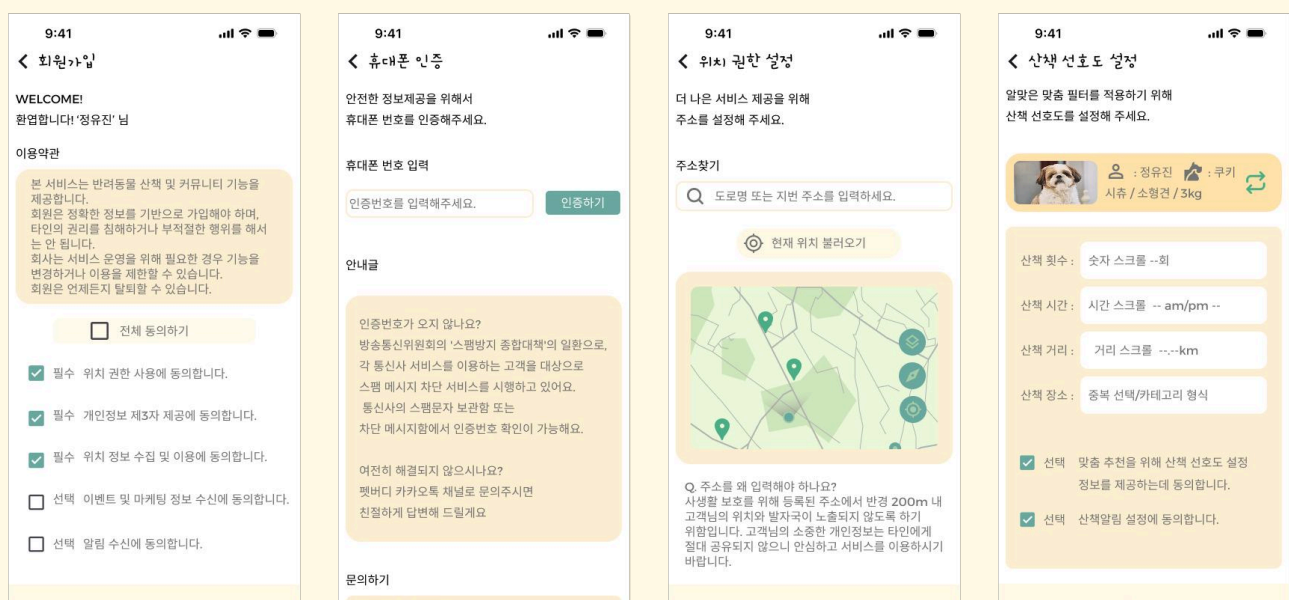
② 회원가입
③ 휴대폰인증
④ 위치권한 설정
⑤ 프로필 설정
9:41

② 회원가입

< 회원가입

WELCOME!
환영합니다! '정유진' 님

이용약관

본 서비스는 반려동물 산책 및 커뮤니티 기능을 제공합니다.
회원은 정확한 정보를 기반으로 가입해야 하며, 타인의 권리를 침해하거나 부적절한 행위를 해서는 안 됩니다.
회사는 서비스 운영을 위해 필요한 경우 기능을 변경하거나 이용을 제한할 수 있습니다.
회원은 언제든지 탈퇴할 수 있습니다.

☐ 전체 동의하기

☑ 필수 위치 권한 사용에 동의합니다.

☑ 필수 개인정보 제3자 제공에 동의합니다.

☑ 필수 위치 정보 수집 및 이용에 동의합니다.

☐ 선택 이벤트 및 마케팅 정보 수신에 동의합니다.

☐ 선택 알림 수신에 동의합니다.

회원가입하기

③ 휴대폰인증

< 휴대폰 인증

안전한 정보제공을 위해서
휴대폰 번호를 인증해주세요.

휴대폰 번호 입력

인증번호를 입력해주세요. 인증하기

안내글

인증번호가 오지 않나요?
방송통신위원회의 '스팸방지 종합대책'의 일환으로,
각 통신사 서비스를 이용하는 고객을 대상으로
스팸 메시지 차단 서비스를 시행하고 있어요.
통신사의 스팸문자 보관함 또는
차단 메시지함에서 인증번호 확인이 가능해요.

여전히 해결되지 않으시나요?
펫버디 카카오톡 채널로 문의주시면
친절하게 답변해 드릴게요

문의하기

카카오톡 문의하기

④ 위치권한 설정

< 위치 권한 설정

더 나은 서비스 제공을 위해
주소를 설정해 주세요.

주소찾기

도로명 또는 지번 주소를 입력하세요.

현재 위치 불러오기

Q. 주소를 왜 입력해야 하나요?
사생활 보호를 위해 등록된 주소에서 반경 200m 내 고객님의 위치와 발자국이 노출되지 않도록 하기 위함입니다. 고객님의 소중한 개인정보는 타인에게 절대 공유되지 않으니 안심하고 서비스를 이용하시기 바랍니다.

입력완료

⑤ 프로필 설정

< 산책 선호도 설정

알맞은 맞춤 필터를 적용하기 위해
산책 선호도를 설정해 주세요.

: 정유진 : 쿠키
시츄 / 소형견 / 3kg

산책 횟수 : 숫자 스크롤 --회
산책 시간 : 시간 스크롤 -- am/pm --
산책 거리 : 거리 스크롤 --.--km
산책 장소 : 중복 선택/카테고리 형식

☑ 선택 맞춤 추천을 위해 산책 선호도 설정 정보를 제공하는데 동의합니다.

☑ 선택 산책알림 설정에 동의합니다.

입력완료

인터랙션

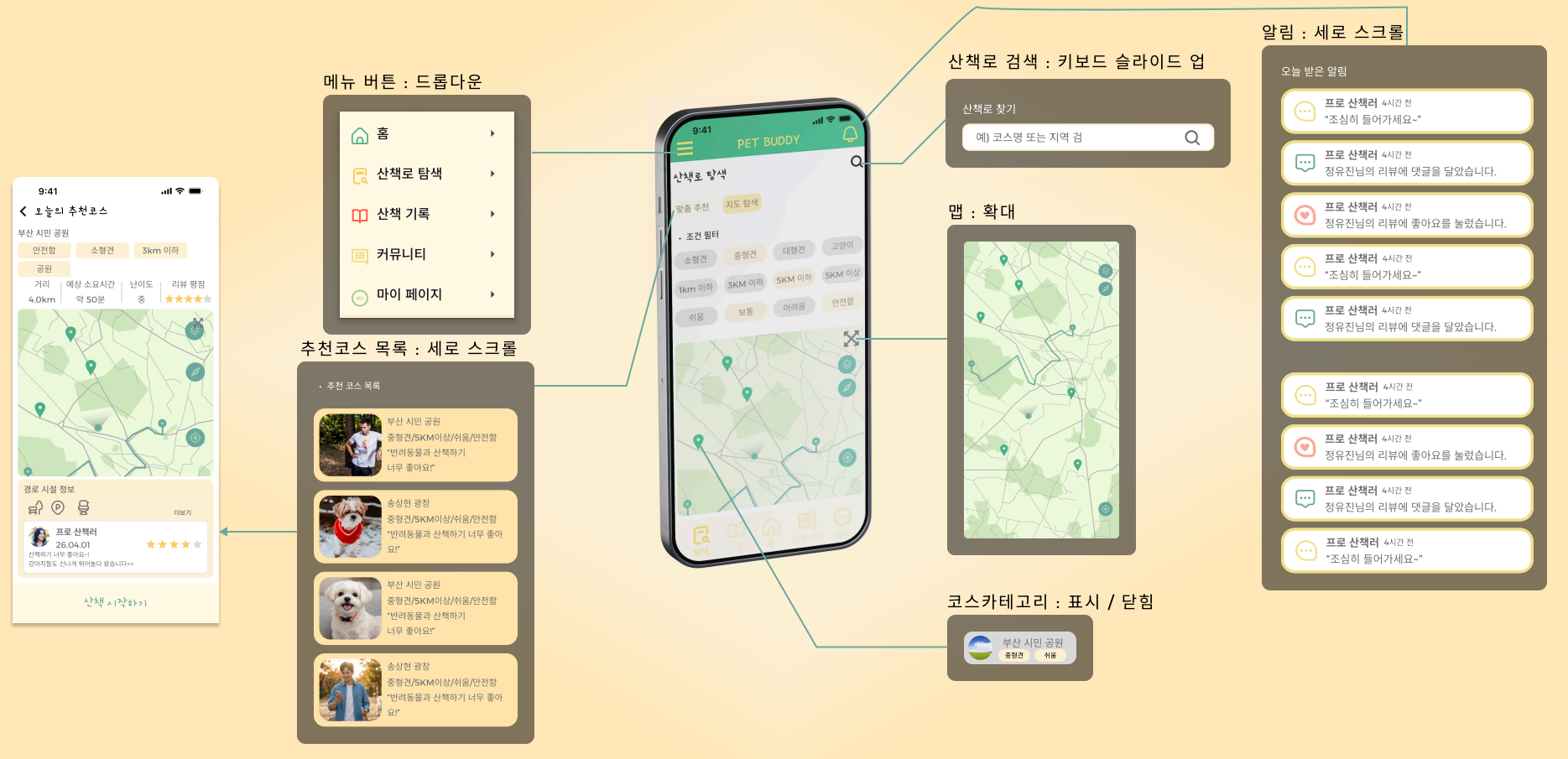
메뉴 버튼 : 드롭다운
홈
산책로 탐색
산책 기록
커뮤니티
마이 페이지
추천코스 목록 : 세로 스크롤
추천 코스 목록
부산 시민 공원
송상현 광장
중형견/5KM이상/쉬움/안전함
"반려동물과 산책하기 너무 좋아요!"
9:41
오늘의 추천코스
부산 시민 공원
안전함
소형견
3km 이하
공원
거리 4.0km
예상 소요시간 약 50분
난이도 중
리뷰 평점
경로 시설 정보
더보기
프로 산책러
26.04.01
산책 시작하기
PET BUDDY
산책로 탐색
맞춤 추천
지도 탐색
조건 필터
소형견
중형견
대형견
고양이
1km 이하
3KM 이하
5KM 이하
5KM 이상
쉬움
보통
어려움
안전함
산책로 검색 : 키보드 슬라이드 업
산책로 찾기
예) 코스명 또는 지역 검
맵 : 확대
코스카테고리 : 표시 / 닫힘
부산 시민 공원
중형견
쉬움
알림 : 세로 스크롤
오늘 받은 알림
프로 산책러 4시간 전
"조심히 들어가세요~"
정유진님의 리뷰에 댓글을 달았습니다.
정유진님의 리뷰에 좋아요를 눌렀습니다.

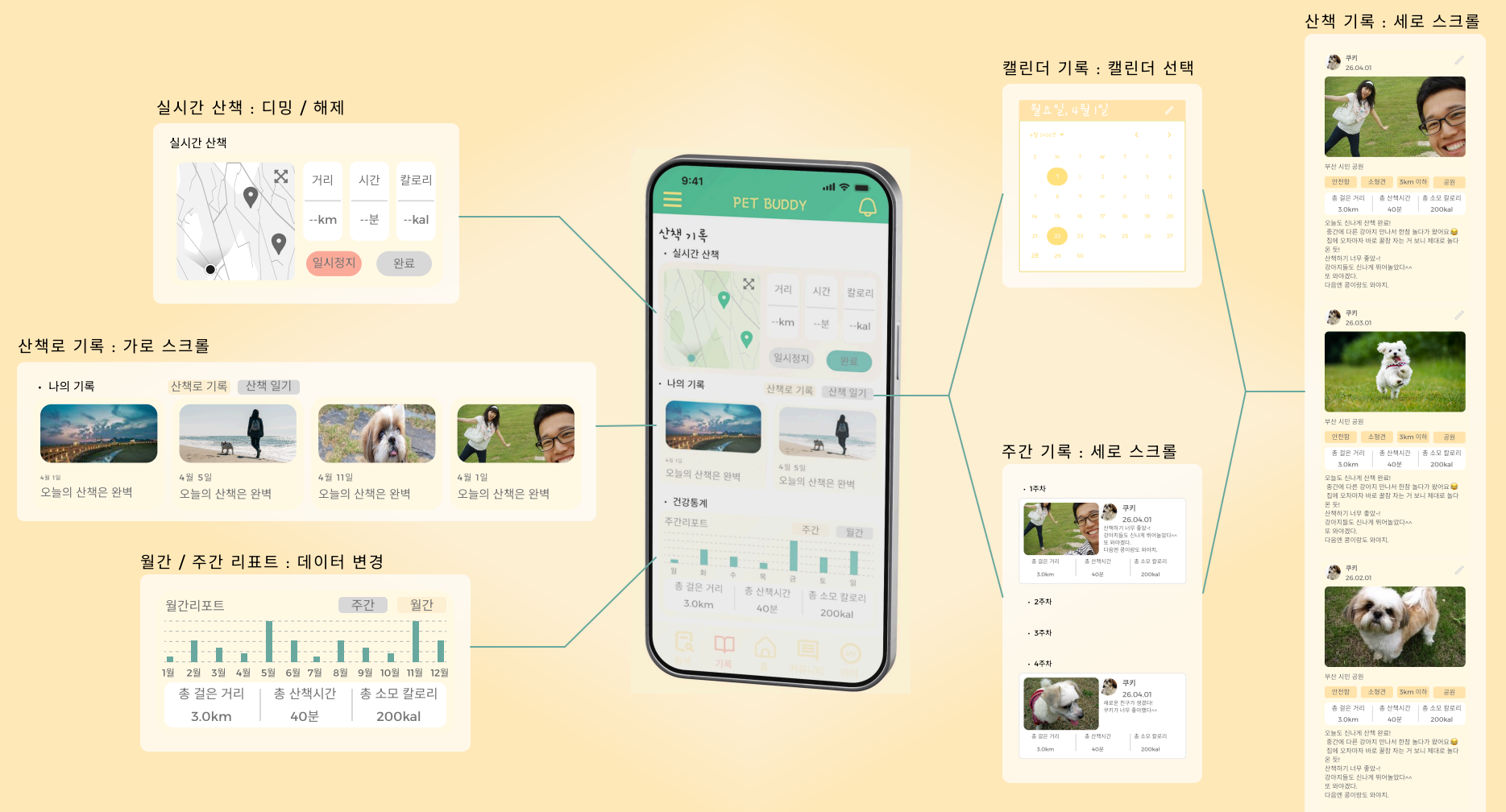
실시간 산책 : 디밍 / 해제
실시간 산책
거리
시간
칼로리
--km
--분
--kal
일시정지
완료
산책로 기록 : 가로 스크롤
나의 기록
산책로 기록
산책 일기
4월 1일
4월 5일
4월 11일
오늘의 산책은 완벽
월간 / 주간 리포트 : 데이터 변경
월간리포트
주간
월간
1월
2월
3월
4월
5월
6월
7월
8월
9월
10월
11월
12월
총 걸은 거리
3.0km
총 산책시간
40분
총 소모 칼로리
200kal
9:41
PET BUDDY
산책 기록
건강통계
주간리포트
캘린더 기록 : 캘린더 선택
월요일, 4월 1일
주간 기록 : 세로 스크롤
1주차
2주차
3주차
4주차
쿠키
26.04.01
산책 기록 : 세로 스크롤
부산 시민 공원
안전함
소형견
3km 이하
공원

사용자 테스트 리스트

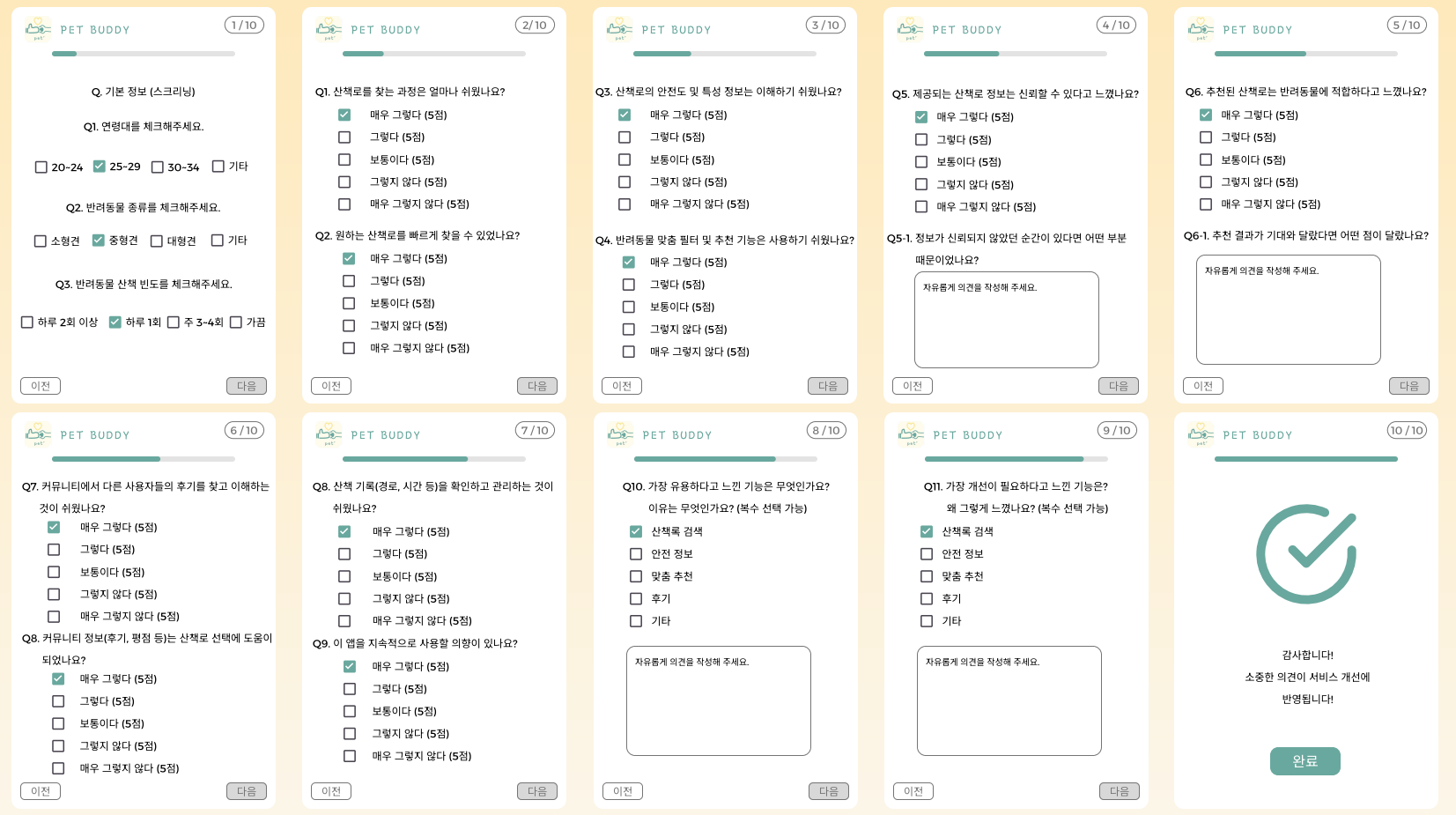

1/10

Q. 기본 정보 (스크리닝)

Q1. 연령대를 체크해주세요.

☐ 20-24 ☑ 25-29 ☐ 30-34 ☐ 기타

Q2. 반려동물 종류를 체크해주세요.

☐ 소형견 ☑ 중형견 ☐ 대형견 ☐ 기타

Q3. 반려동물 산책 빈도를 체크해주세요.

☐ 하루 2회 이상 ☑ 하루 1회 ☐ 주 3-4회 ☐ 가끔

이전 다음

2/10

Q1. 산책로를 찾는 과정은 얼마나 쉬웠나요?

☑ 매우 그렇다 (5점)
☐ 그렇다 (5점)
☐ 보통이다 (5점)
☐ 그렇지 않다 (5점)
☐ 매우 그렇지 않다 (5점)

Q2. 원하는 산책로를 빠르게 찾을 수 있었나요?

☑ 매우 그렇다 (5점)
☐ 그렇다 (5점)
☐ 보통이다 (5점)
☐ 그렇지 않다 (5점)
☐ 매우 그렇지 않다 (5점)

이전 다음

3/10

Q3. 산책로의 안전도 및 특성 정보는 이해하기 쉬웠나요?

☑ 매우 그렇다 (5점)
☐ 그렇다 (5점)
☐ 보통이다 (5점)
☐ 그렇지 않다 (5점)
☐ 매우 그렇지 않다 (5점)

Q4. 반려동물 맞춤 필터 및 추천 기능은 사용하기 쉬웠나요?

☑ 매우 그렇다 (5점)
☐ 그렇다 (5점)
☐ 보통이다 (5점)
☐ 그렇지 않다 (5점)
☐ 매우 그렇지 않다 (5점)

이전 다음

4/10

Q5. 제공되는 산책로 정보는 신뢰할 수 있다고 느꼈나요?

☑ 매우 그렇다 (5점)
☐ 그렇다 (5점)
☐ 보통이다 (5점)
☐ 그렇지 않다 (5점)
☐ 매우 그렇지 않다 (5점)

Q5-1. 정보가 신뢰되지 않았던 순간이 있다면 어떤 부분 때문이었나요?

자유롭게 의견을 작성해 주세요.

이전 다음

5/10

Q6. 추천된 산책로는 반려동물에 적합하다고 느꼈나요?

☑ 매우 그렇다 (5점)
☐ 그렇다 (5점)
☐ 보통이다 (5점)
☐ 그렇지 않다 (5점)
☐ 매우 그렇지 않다 (5점)

Q6-1. 추천 결과가 기대와 달랐다면 어떤 점이 달랐나요?

자유롭게 의견을 작성해 주세요.

이전 다음

6/10

Q7. 커뮤니티에서 다른 사용자들의 후기를 찾고 이해하는 것이 쉬웠나요?

☑ 매우 그렇다 (5점)
☐ 그렇다 (5점)
☐ 보통이다 (5점)
☐ 그렇지 않다 (5점)
☐ 매우 그렇지 않다 (5점)

Q8. 커뮤니티 정보(후기, 평점 등)는 산책로 선택에 도움이 되었나요?

☑ 매우 그렇다 (5점)
☐ 그렇다 (5점)
☐ 보통이다 (5점)
☐ 그렇지 않다 (5점)
☐ 매우 그렇지 않다 (5점)

이전 다음

7/10

Q8. 산책 기록(경로, 시간 등)을 확인하고 관리하는 것이 쉬웠나요?

☑ 매우 그렇다 (5점)
☐ 그렇다 (5점)
☐ 보통이다 (5점)
☐ 그렇지 않다 (5점)
☐ 매우 그렇지 않다 (5점)

Q9. 이 앱을 지속적으로 사용할 의향이 있나요?

☑ 매우 그렇다 (5점)
☐ 그렇다 (5점)
☐ 보통이다 (5점)
☐ 그렇지 않다 (5점)
☐ 매우 그렇지 않다 (5점)

이전 다음

8/10

Q10. 가장 유용하다고 느낀 기능은 무엇인가요? 이유는 무엇인가요? (복수 선택 가능)

☑ 산책록 검색
☐ 안전 정보
☐ 맞춤 추천
☐ 후기
☐ 기타

자유롭게 의견을 작성해 주세요.

이전 다음

9/10

Q11. 가장 개선이 필요하다고 느낀 기능은? 왜 그렇게 느꼈나요? (복수 선택 가능)

☑ 산책록 검색
☐ 안전 정보
☐ 맞춤 추천
☐ 후기
☐ 기타

자유롭게 의견을 작성해 주세요.

이전 다음

10/10

감사합니다!
소중한 의견이 서비스 개선에
반영됩니다!

완료

사용자 테스트 시나리오

테스트 목적	산책로 탐색의 속도와 직관성 정보(안전/특성)의 이해도 및 신뢰성 맞춤 추천의 정확성 커뮤니티/기록 기능의 실사용 가치 전체 서비스의 지속 사용 가능성	테스트 상황 설정 (공통 안내) 당신은 평소 반려동물과 산책을 자주 하는 사용자입니다. 오늘 새로운 산책로를 찾기 위해 이 앱을 처음 사용하게 되었습니다.

	시나리오 1	시나리오 2	시나리오 3	시나리오 4	시나리오 5	시나리오 6
	산책로 탐색	산책로 정보 확인	맞춤 추천 사용	커뮤니티 활용	산책 기록 확인	전체 사용 평가
목표	원하는 산책로를 찾는다	산책로의 안전성과 특성을 이해한다	내 반려동물에 맞는 산책로를 찾는다	다른 사용자 후기를 참고해 판단한다	산책 기록 기능을 이해하고 활용한다	서비스 전반에 대해 판단한다
수행과제	1. 현재 위치 기준으로 산책로를 탐색해보세요 2. 마음에 드는 산책로 1곳을 선택해주세요	1. 선택한 산책로의 상세 정보를 확인해주세요 2. 해당 산책로가 안전하다고 판단되는지 스스로 결정해주세요	1. 자신의 반려동물에 맞게 조건을 설정해주세요 (예: 크기, 활동량 등) 2. 추천된 산책로 중 하나를 선택해주세요	1. 선택한 산책로의 후기를 확인해주세요 2. 후기를 보고 해당 산책로를 갈지 최종 결정해주세요	1. 이전 산책 기록을 확인해보세요 (또는 기록 기능을 탐색) 2. 기록 기능을 어떻게 활용할 수 있을지 생각해보세요	1. 지금까지 사용한 경험을 바탕으로 “이 앱을 계속 사용할지” 판단해주세요
관찰포인트	1. 탐색 경로 (지도 vs 검색 vs 추천) 2. 망설임/되돌아가기 발생 여부 3. 소요 시간	1. 어떤 정보를 먼저 보는가 2. 이해 못하고 지나치는 요소 3. 신뢰 판단 기준	1. 필터 이해도 2. 추천 결과 만족도 3. 기대 vs 실제 차이	1. 어떤 콘텐츠 (사진/글/평점)를 보는지 2. 후기 신뢰 여부	1. 기능 발견 가능성 2. 이해도 3. 실제 사용 의지	

사용자 반응 기록지

사용자 반응 기록지 (UX 테스트 관찰 체크리스트)

🧾 기본 정보
테스트 참여자 ID:
테스트 일시:
반려동물 유형:
테스트 환경: (모바일 / PC)

1. 산책로 탐색

✓ 수행 여부
☐ 성공 ☐ 부분 성공 ☐ 실패

✓ 소요 시간
_____ 초 / 분

✓ 행동 관찰
☐ 검색 기능 사용
☐ 지도 탐색
☐ 추천 리스트 사용
☐ 뒤로가기/반복 탐색 발생

✓ 문제 발생 여부
☐ 없음 ☐ 있음 → 내용:
____

✓ 사용자의 반응
☐ 망설임 ☐ 혼란
☐ 자연스러움 ☐ 빠른 결정

✓ 주요 발화 (Think Aloud)

→ “______________________”

2. 산책로 정보 확인

✓ 수행 여부

☐ 성공 ☐ 부분 성공 ☐ 실패

✓ 행동 관찰

☐ 안전 정보 확인
☐ 거리/시간 확인
☐ 사진 확인
☐ 후기 확인

✓ 문제 발생 여부

☐ 없음 ☐ 있음 → 내용:
____

✓ 이해도 반응

☐ 바로 이해 ☐ 일부 이해 ☐ 이해 어려움

✓ 신뢰 반응

☐ 신뢰 ☐ 의심 ☐ 판단 유보

✓ 주요 발화

→ “______________________”

3. 맞춤 추천 기능

✓ 수행 여부

☐ 성공 ☐ 부분 성공 ☐ 실패

✓ 행동 관찰

☐ 필터 설정 시도
☐ 설정 없이 추천 사용
☐ 옵션 변경 반복

✓ 문제 발생 여부

☐ 없음 ☐ 있음 → 내용:
____

✓ 반응

☐ 이해 쉬움 ☐ 헷갈림 ☐ 사용 포기

✓ 기대 vs 결과

☐ 기대와 일치 ☐ 일부 일치 ☐ 불일치

✓ 주요 발화

→ “______________________”

4. 커뮤니티 기능

✓ 수행 여부

☐ 성공 ☐ 부분 성공 ☐ 실패

✓ 행동 관찰

☐ 후기 읽음
☐ 사진 확인
☐ 평점 확인
☐ 스킵

✓ 문제 발생 여부

☐ 없음 ☐ 있음 → 내용:
____

✓ 반응

☐ 신뢰 ☐ 참고만 ☐ 무시

✓ 선택 영향 여부

☐ 영향 있음 ☐ 영향 없음

✓ 주요 발화

→ “______________________”

5. 산책 기록 기능

✓ 수행 여부

☐ 성공 ☐ 부분 성공 ☐ 실패

✓ 행동 관찰

☐ 기록 확인
☐ 기능 탐색만
☐ 사용 안함

✓ 문제 발생 여부

☐ 없음 ☐ 있음 → 내용:
____

✓ 반응

☐ 유용함 ☐ 보통 ☐ 필요 없음

✓ 주요 발화

→ “______________________”

📊 종합 평가 (관찰 기반)

✓ 전반적 사용 흐름

☐ 매우 자연스러움
☐ 보통
☐ 불편함 많음

✓ 주요 문제 유형 (중복 선택 가능)

☐ 탐색 어려움
☐ 정보 이해 부족
☐ 정보 신뢰 부족
☐ 추천 정확도 낮음
☐ UI 혼란
☐ 기능 발견 어려움

🧠 인사이트 메모 (가장 중요)

👉 관찰자가 직접 해석해서 작성

가장 큰 문제점:
→ ______________________
가장 긍정적인 요소:
→ ______________________
개선이 시급한 기능:
→ ______________________

페인포인트 분석 및 보완

단계	산책로 탐색	산책로 정보 확인	맞춤 추천 사용	커뮤니티 활용	산책 기록 확인
페인포인트	산책로 탐색경로를 찾기 어려움	산책로 상세에 평균 리뷰로 도출된 카테고리로 산책로 파악 및 신뢰성은 있으나 카테고리 자체가 눈에 잘 띄지 않음	설정없이 맞춤 추천되는 산책로가 탐색메뉴가 아닌 홈메뉴에서 가능함	인기/추천 리뷰의 산책로가 ‘좋아요’ 순이라 지역 범위 설정이 필요함	산책로 리뷰와 산책기록 기능이 너무 비슷해서 필요성이 떨어짐
보완	1. 하단 바에 메뉴별 메뉴명 기입 2. ui로 복잡성 줄이기	1. 카테고리 크기와 색상 변경	1. 맞춤 추천에서 프로필에 맞는 사전 설정이 되도록 기능 설계	1. 인기/추천 리뷰 산책로 ‘좋아요’ 순과 거리순 추가	1. 산책기록 기능 추가 2. 산책완료시 달성한 뱃지나 업적 등 띄우기
종합평가	가장 큰문제점:ui 부족-글이 많아서 기능이 복잡하고 한눈에 안보임 가장 긍정적인 요소: 요소가 간단하고 접근성이 좋게 구성돼있음 개선이 시급한 기능: 산책기록과 리뷰의 차별점				

평가

기대 효과

1. 사용자들이 새로운 산책로를 쉽고 빠르게 찾아서 산책로 검색에 피로감이 줄어든다.
2. 반려동물의 특성에 따라 맞춤 설정을 통해 개별화된 산책로를 즐길 수 있다.
3. 산책로의 시설과 안전도를 직관적으로 파악할 수 있어 사용자와 반려동물이 안전한 산책을 할 수 있다.
4. 산책 기록과 산책로 리뷰를 기록하고 공유함으로써 다른 반려인들과 공감대를 형성할 수 있다.

확장 방향

1. 산책로의 안전성과 시설에 대한 더 다양한 정보를 사용자들의 실시간 데이터로 축적해서 지속적인 업데이트
2. 사용자의 증가에 따라 다양한 이벤트 및 마켓과의 협업
3. 반려동물의 건강관리에 관한 세부 기능 추가

개선점

1. 산책기록과 리뷰의 차별점
산책기록과 산책로 리뷰의 기능이 거의 동일하고 UI 또한 비슷한 부분이 많아 차별화된 기능 보완이 필요함
→ 산책 기록에 사용자가 꾸밀 수 있는 디자인 기능 요소 추가
2. 텍스트요소가 많아서 접근성은 높일 수 있으나 과도한 텍스트로 사용감에 피로도가 생기고 지루함
→ 텍스트 요소 검토 후 메타포, UI로 변환

9:41 AM
감사합니다.
pet
시작하기